

Это из "Locus Map user guide"

Measuring distance&area

Cursor to position line

(линия от курсора до текущей позиции)

Another method of easy measuring of the distance between your actual GPS position and any point on the map.

go to Settings > Maps > Auxiliary graphics > Cursor to position line - switch it ON

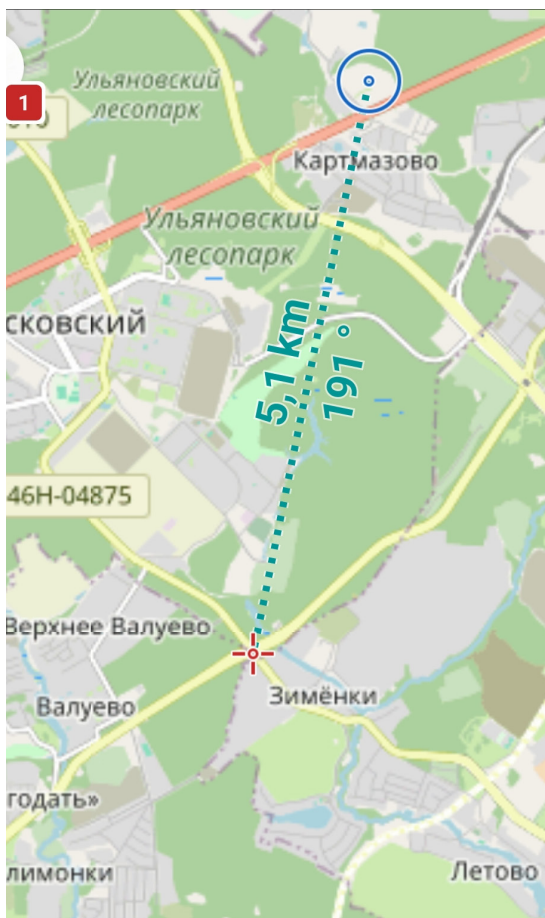
a line with the distance and azimuth stretches between your position and the map cursor



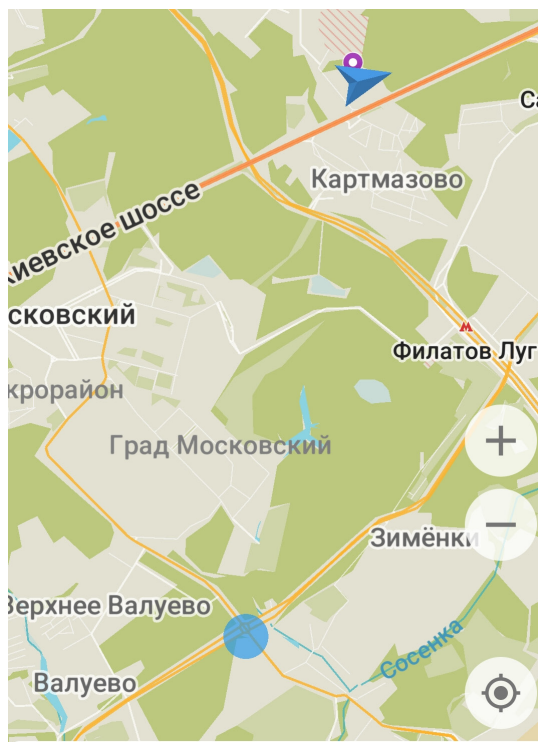
Как по мне так действительно удобно - в реальном времени смотришь карту и сразу видишь расстояние и угол до нужной точки. Справедливо и обратное - зная расстояние и угол легко найти точку.

одно и то же место:

Locus Map



Organic Maps



Неизвестное место

55.57627, 37.375817



5,1 км



ОТЮДА



СОХРАНИТЬ



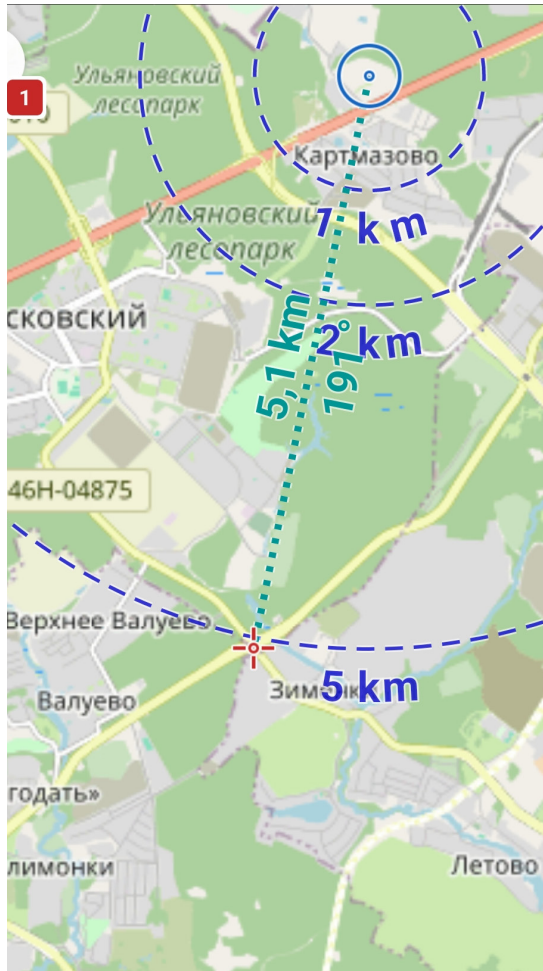
СЮДА

может можно будет в Organic Maps выводить значение угла в панель информации под картой ?

Чтобы не переключаться для узнавания угла направления на каждую новую точку через нажатие на синюю стрелку для перевода ее в полноэкранный режим?

Что еще есть на эту тему в Locus Map

Круги расстояний от текущей позиции. Личное мнение - скорее это прикольно чем полезно. Разве что размечать позиции для круговой обороны?



Определение расстояния между двумя любыми точками на карте нажатием на нее двумя пальцами

